Aviso de confidencialidade: conteúdo de propriedade intelectual do Poliedro Educação e suas unidades de negócios.
Não deve ser copiado, compartilhado ou reproduzido sem o consentimento e autorização formal do Poliedro.

Aviso de confidencialidade: conteúdo de propriedade intelectual do Poliedro Educação e suas unidades de negócios.
Não deve ser copiado, compartilhado ou reproduzido sem o consentimento e autorização formal do Poliedro.

Aviso de confidencialidade: conteúdo de propriedade intelectual do Poliedro Educação e suas unidades de negócios.
Não deve ser copiado, compartilhado ou reproduzido sem o consentimento e autorização formal do Poliedro.

Poliedro
Curso

Aviso de confidencialidade: conteúdo de propriedade intelectual do Poliedro Educação e suas unidades de negócios.
Não deve ser copiado, compartilhado ou reproduzido sem o consentimento e autorização formal do Poliedro.

Poliedro
Curso

Aula 3 – Localização Espacial

Profª Cris – Geografia

Aviso de confidencialidade: conteúdo de propriedade intelectual do Poliedro Educação e suas unidades de negócios.
Não deve ser copiado, compartilhado ou reproduzido sem o consentimento e autorização formal do Poliedro.



Complete

01

HOJE TEMOS A SEGUINTE UTILIZAÇÃO

Todo mapa é uma visão _____AÉREA_____, de um território _____REAL_____ de forma_____REDUZIDA_____.

Essa _____REDUÇÃO_____ é exata (matemática) e confere aos mapas sua utilidade, porque fornece a precisa dimensão do_____REAL_____. A redução é chamada de _____ESCALA_____.

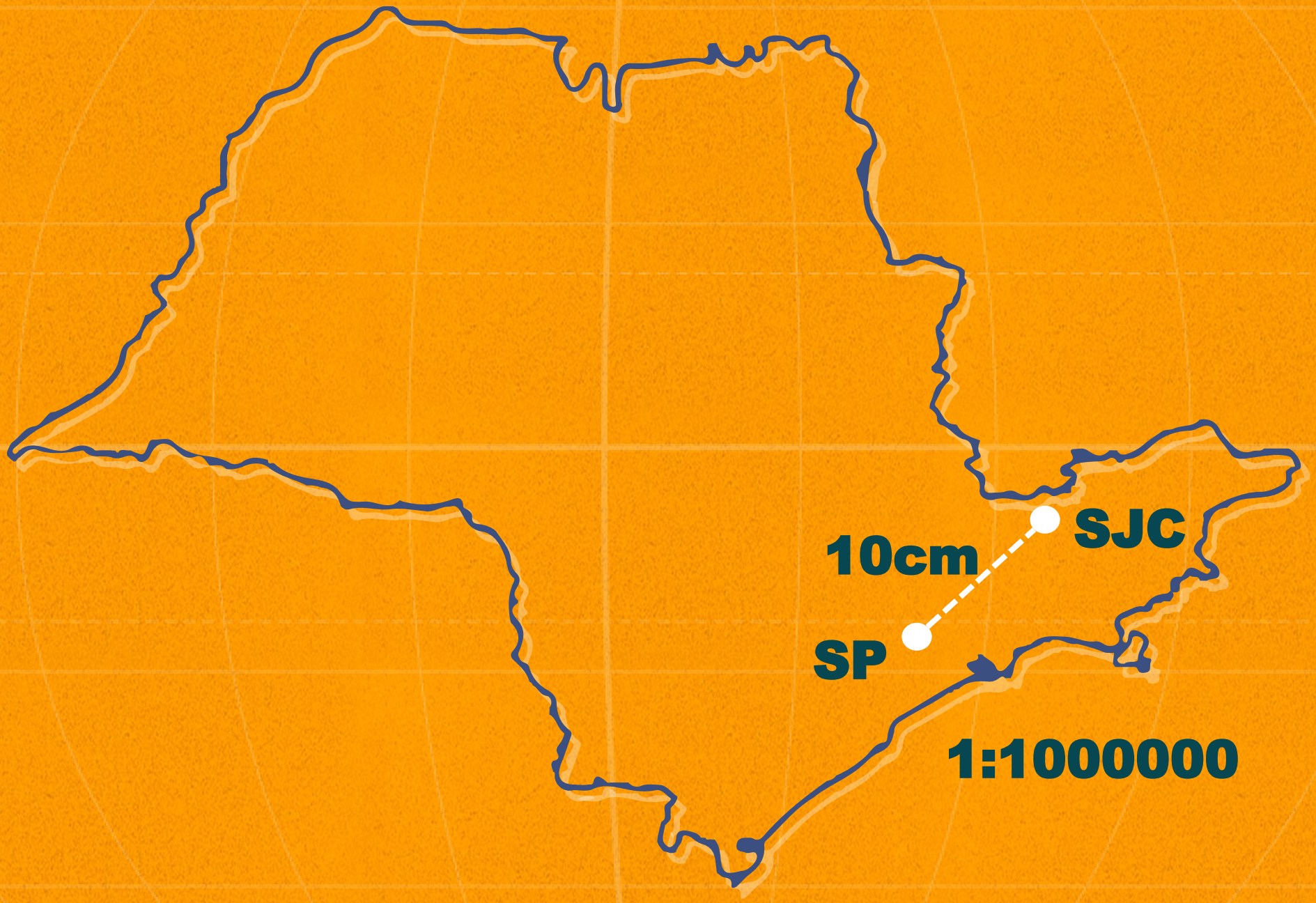
SJC
10cm
SP
1:1000000

Complete

02

DIMENSÕES DA ESCALA:

Quanto __MENOR__ a redução, __MAIOR__ será a riqueza de detalhe.
Essa escala é chamada de __GRANDE__. Ex: 1: 1000.

Quanto __MAIOR__ a redução, __MENOR__ será a riqueza de detalhes.
Essa escala é chamada de __PEQUENA__. Ex: 1: 100000000.

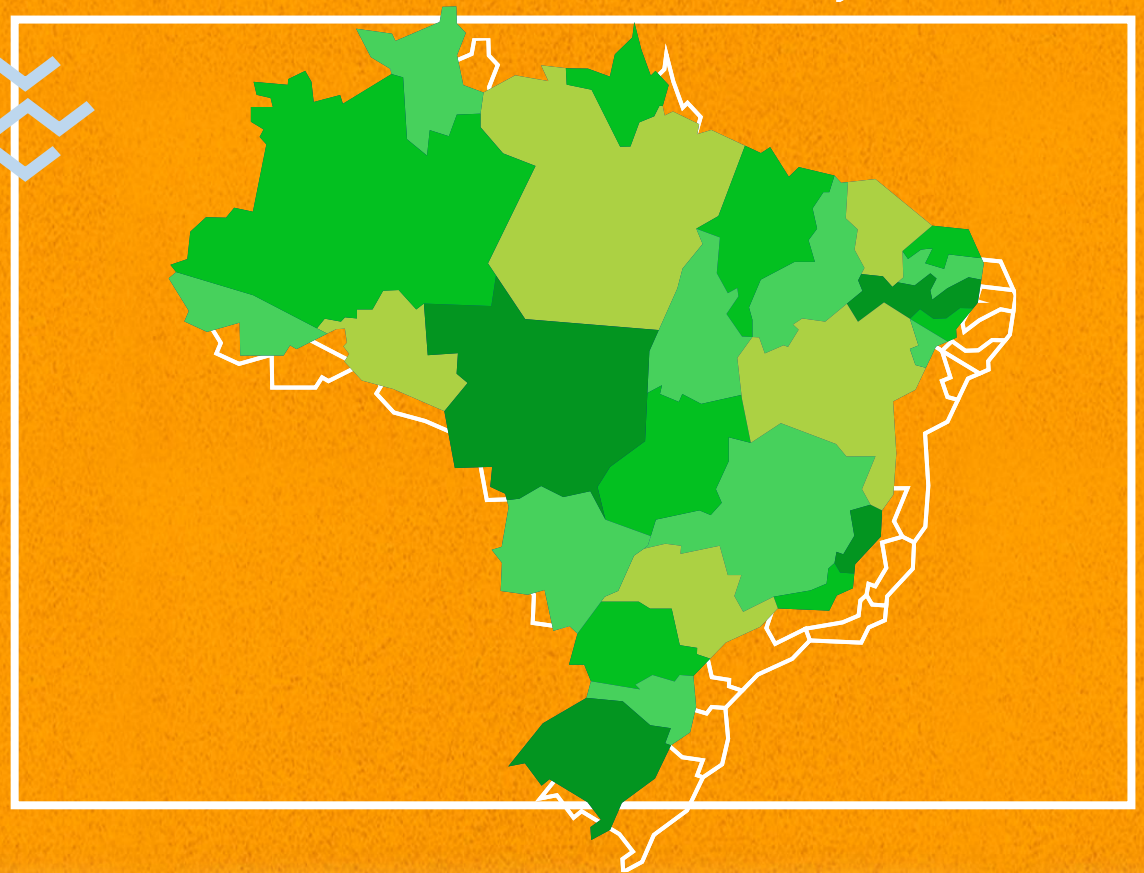

OCEANO
ATLÂNTICO

Complete

03

	América do Sul 1:1000000000	ESCALA PEQUENA
	Brasil 1:100000000	ESCALA PEQUENA
	Cidade de SP 1:1000000	ESCALA GRANDE

SÍMBOLO DA ONU

PROJEÇÕES

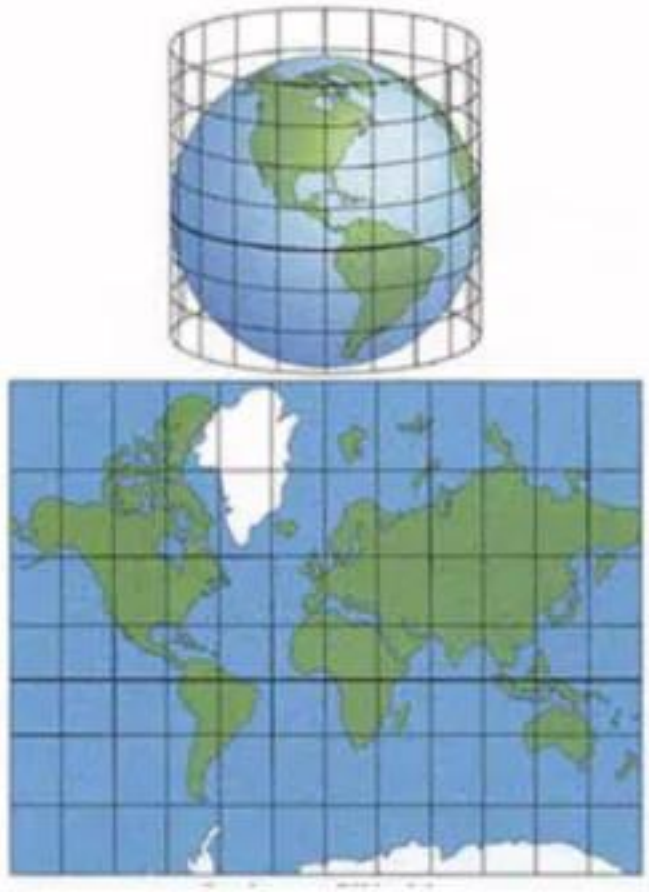

CILÍNDRICA

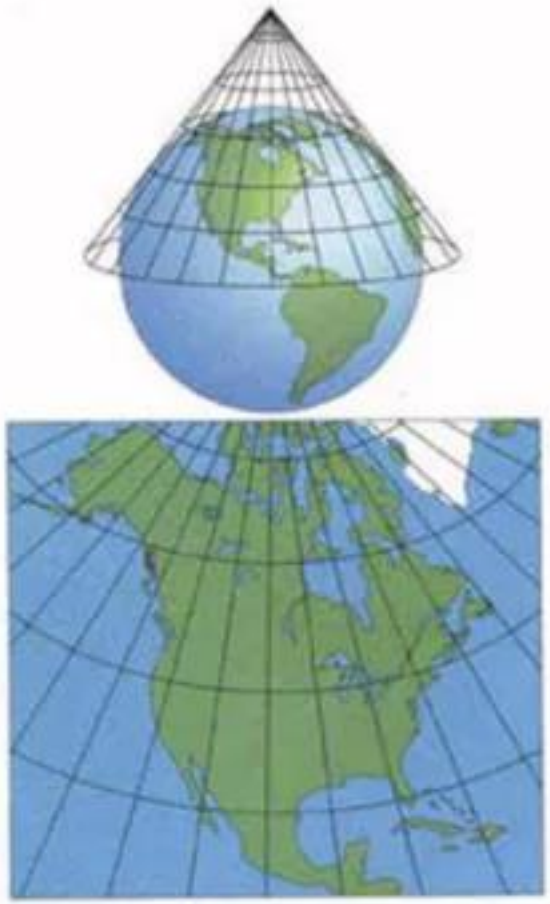

CÔNICA

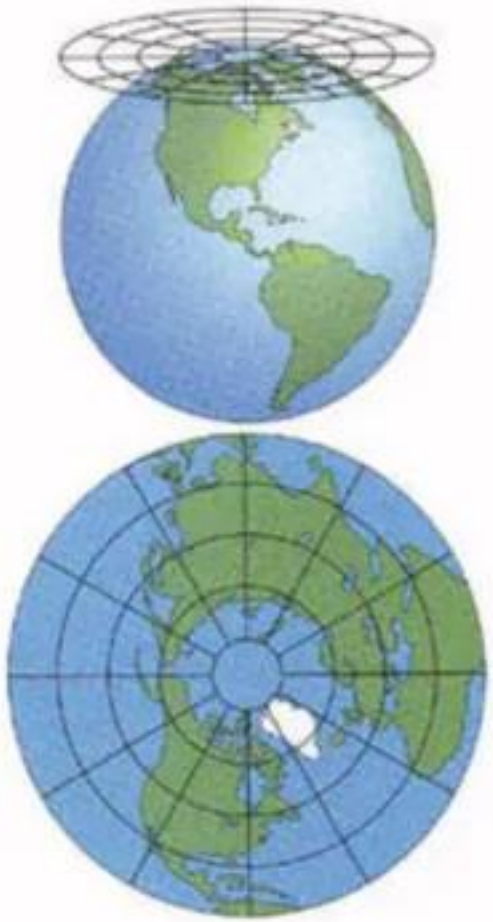

PLANA

(AZIMUTAL)

PROJEÇÃO DE MERCATOR

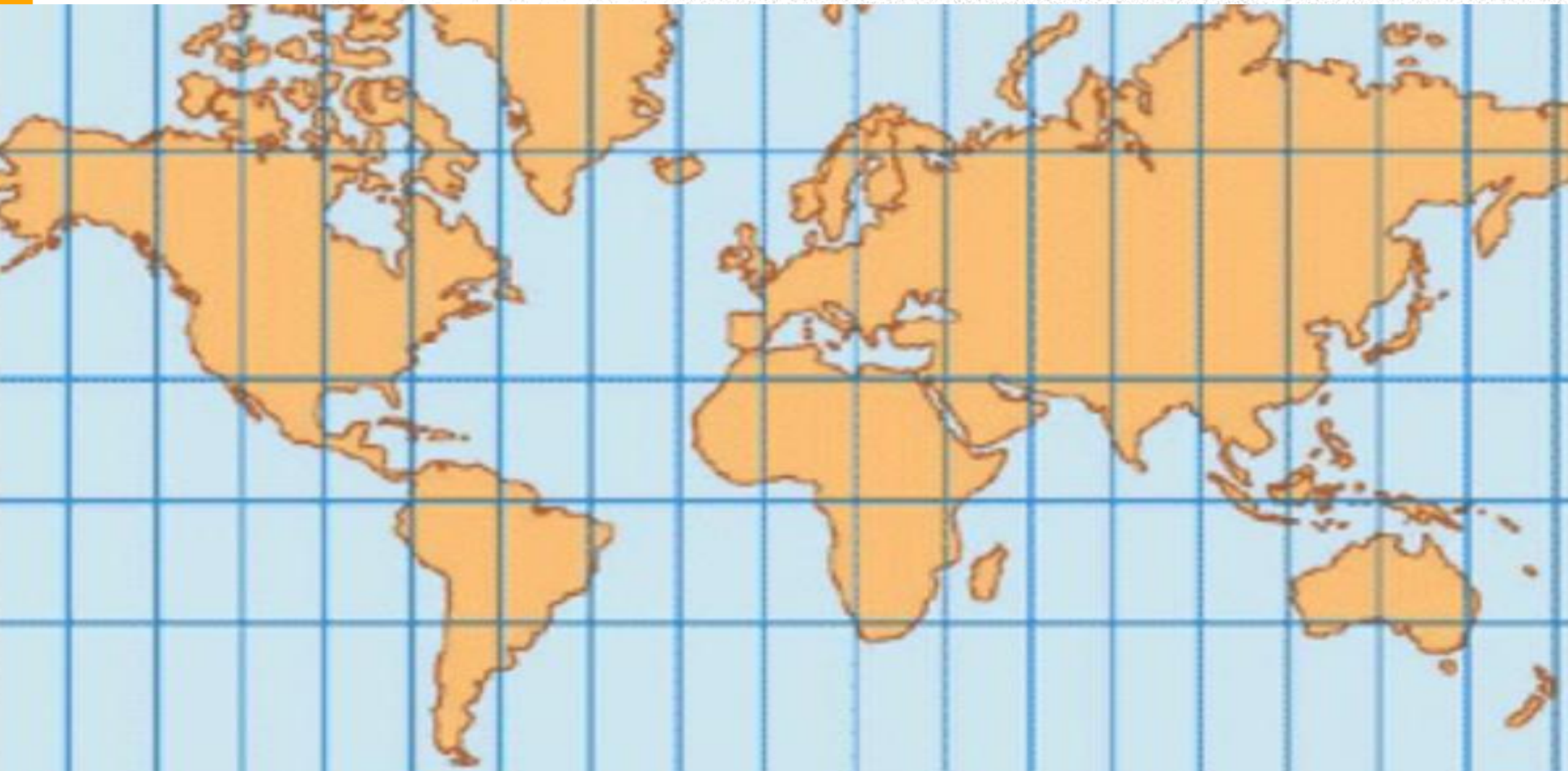

PROJEÇÃO PETERS

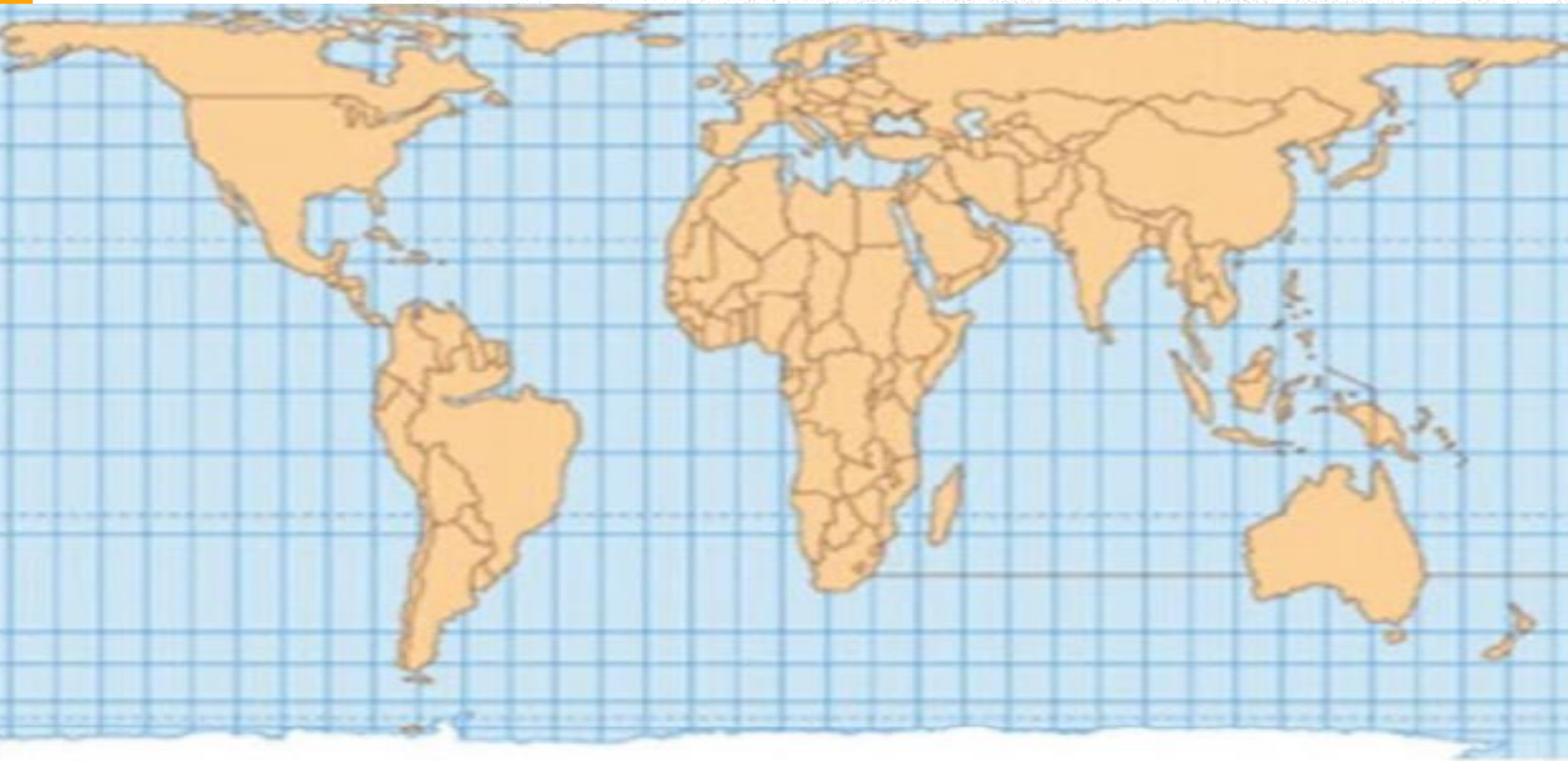

PROJEÇÃO DE PETERS

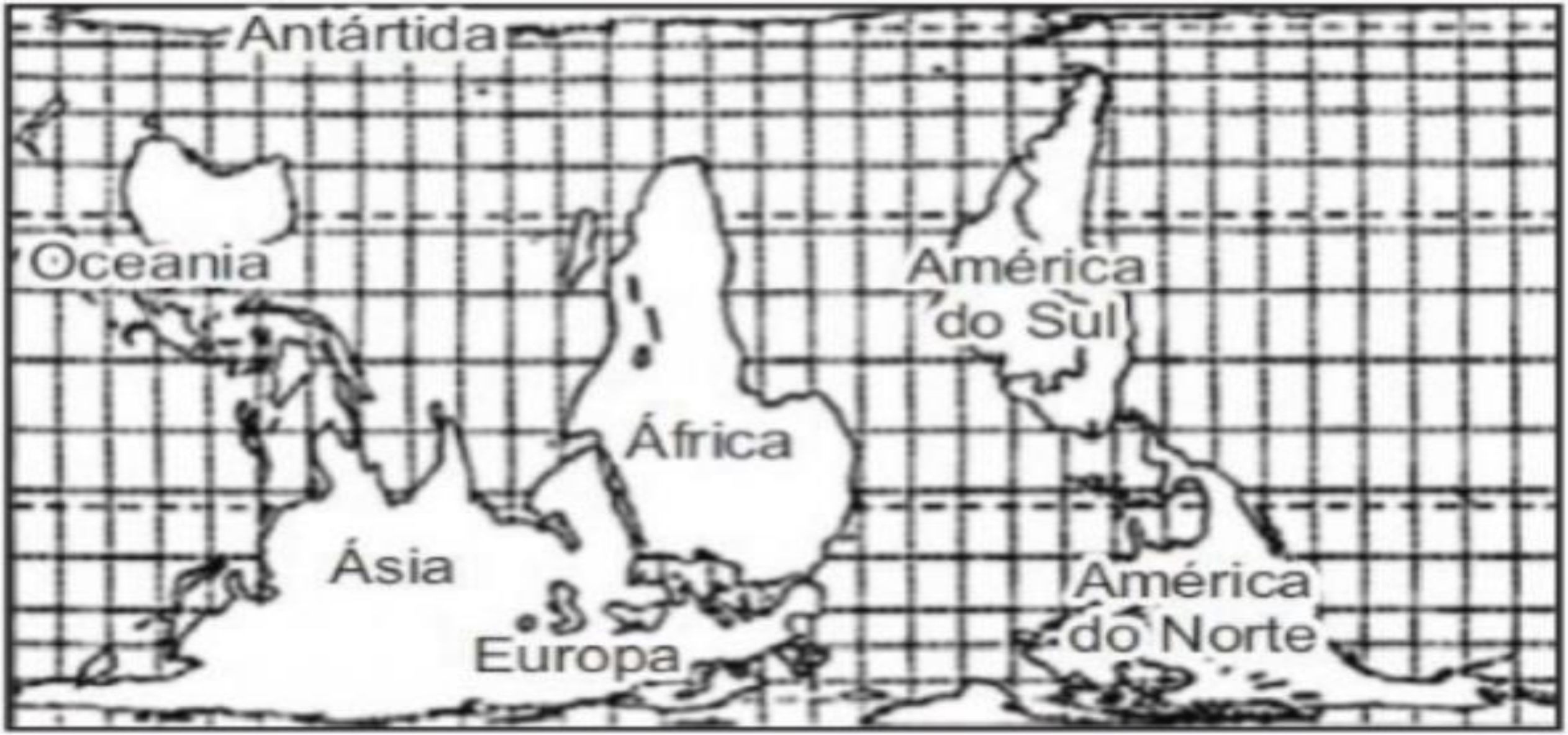

PROJEÇÃO PLANA POLAR AZIMUTAL EQUIDISTANTE

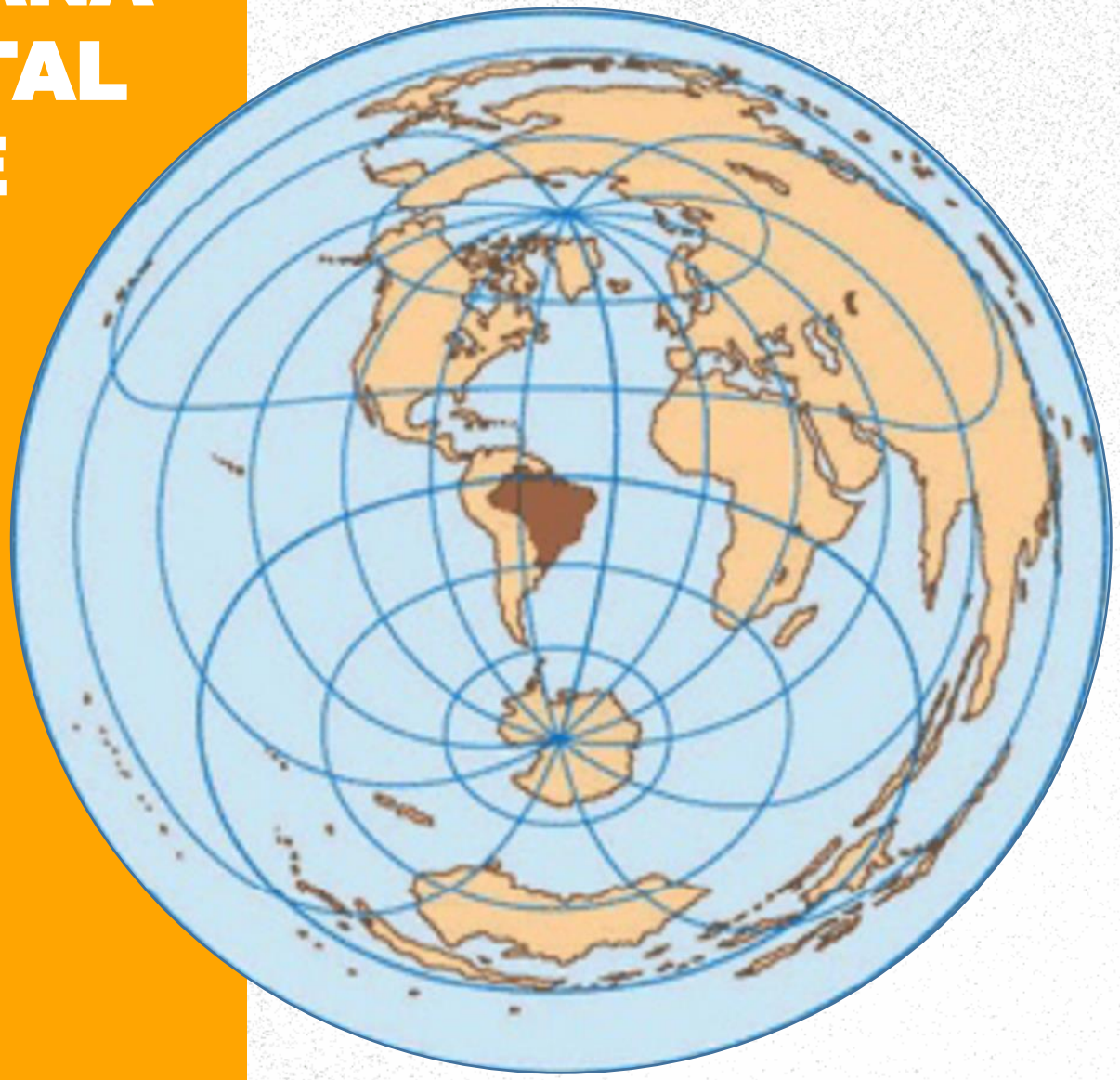

Poliedro
Curso

PROJEÇÃO AFILÁTICA

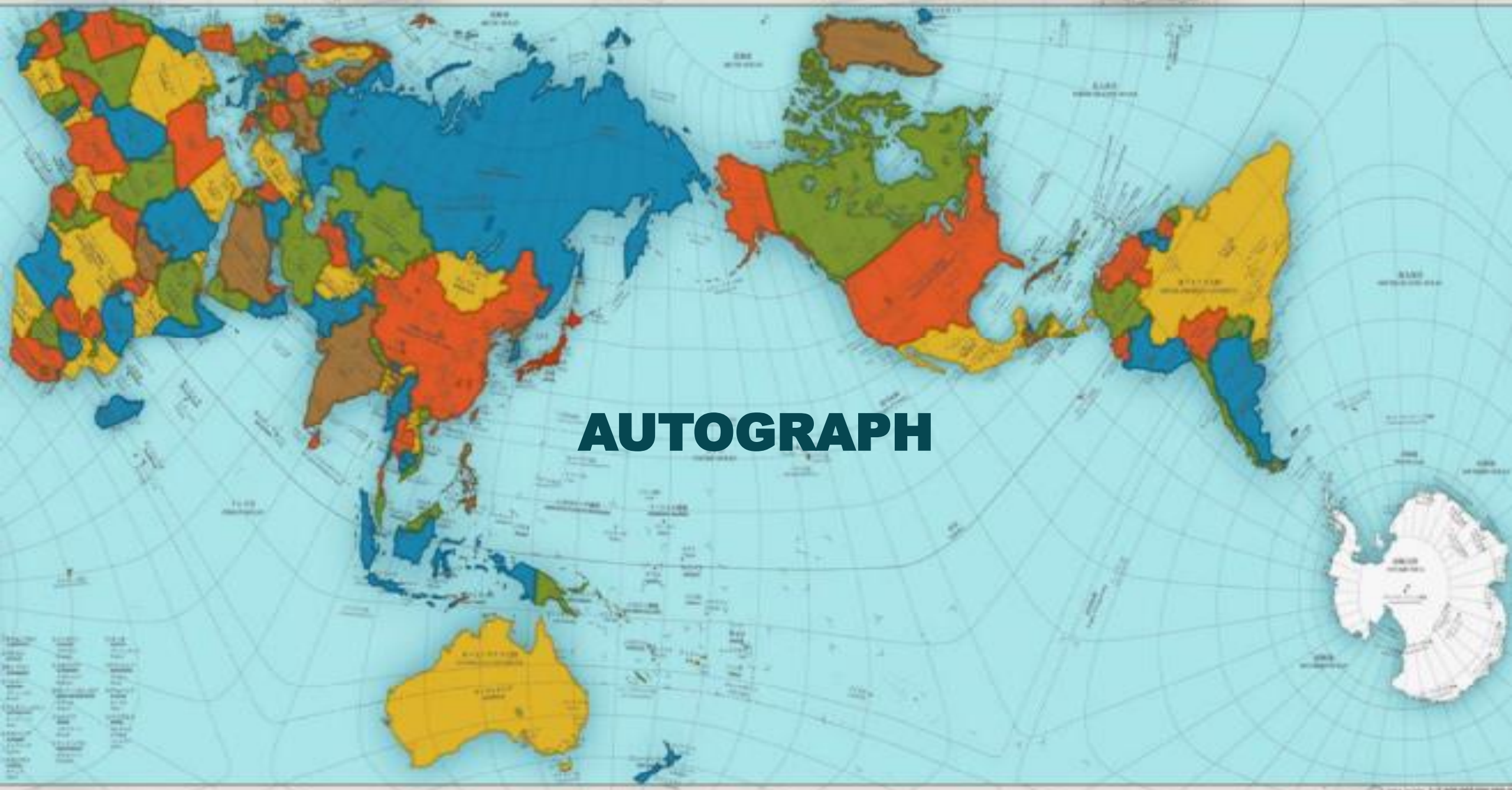

AUTOGRAPH

PROJEÇÃO DE PRINCETON

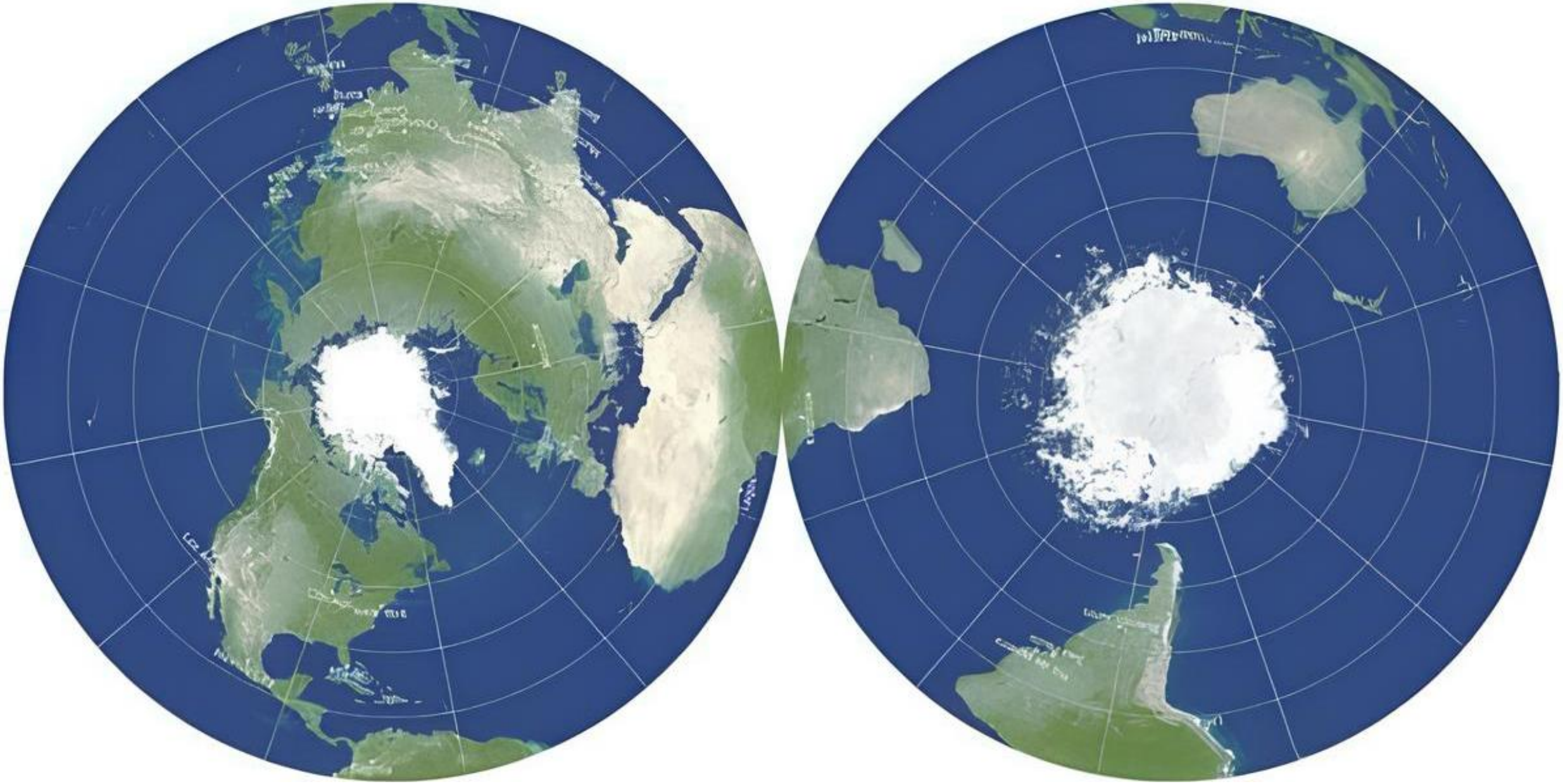

Mapa Mundi IBGE

Notas:
1 - O reconhecimento da soberania dos territórios segue as políticas adotadas pelo governo brasileiro.
2 - O governo brasileiro não reconhece a soberania do Marrocos sobre o território localizado ao sul deste.
3 - Não estão representadas eventuais disputas de fronteiras entre países.

Atualizado em setembro/2024

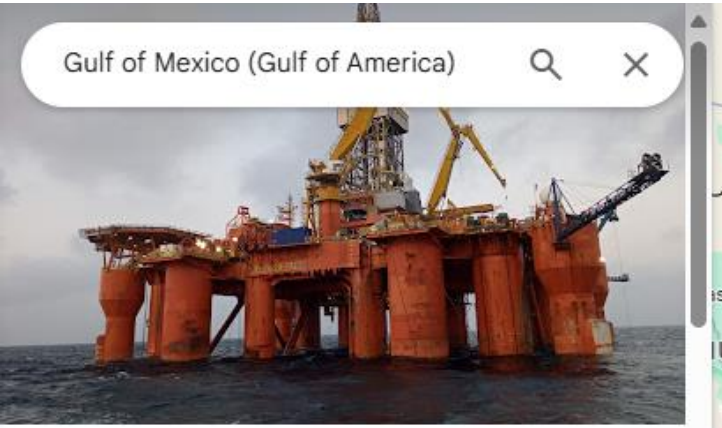

Gulf of Mexico (Gulf of America)

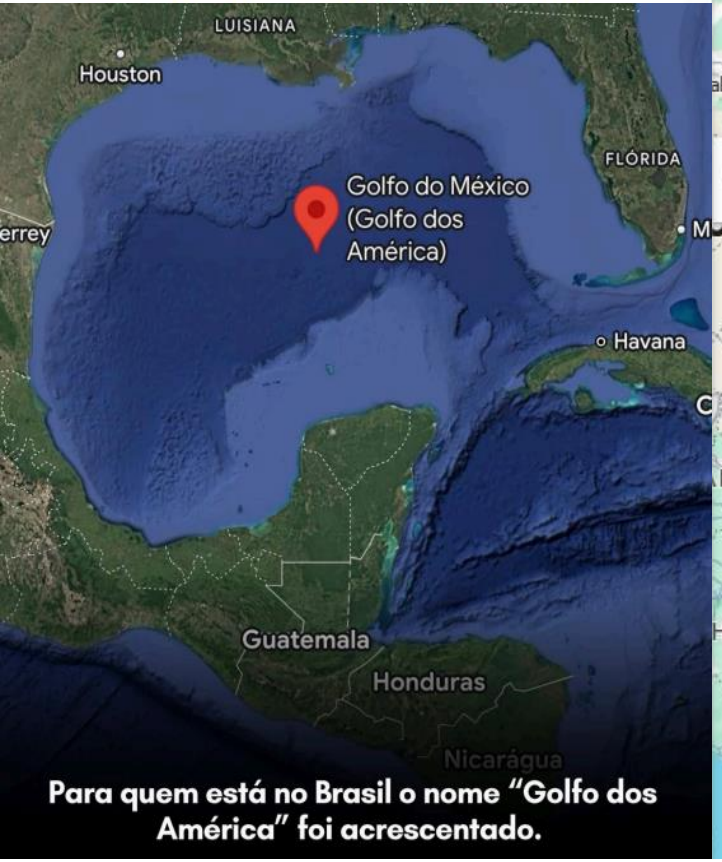

Para quem está no Brasil o nome "Golfo dos América" foi acrescentado.

Golfo do México

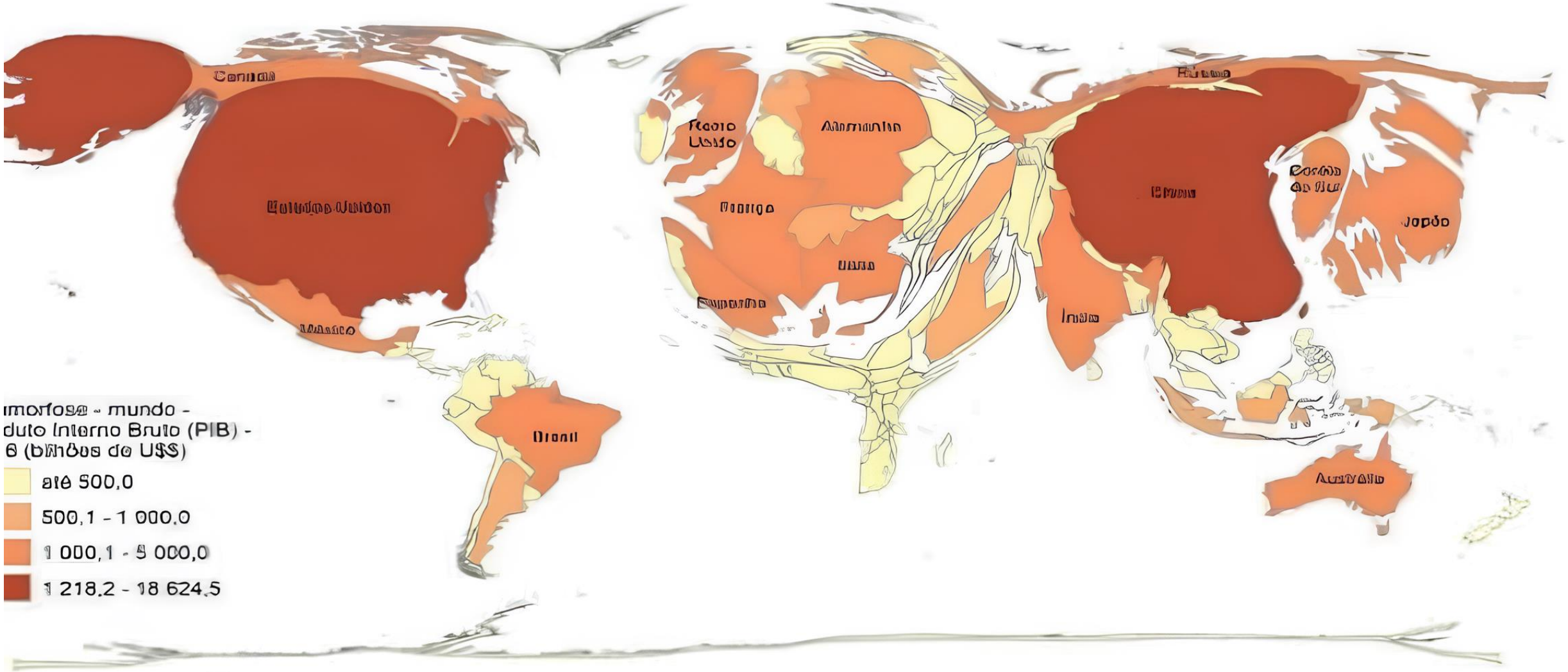

5.

Fonte: National Accounts Main Aggregates Database, United Nations (UN). Disponível em: <https://educa.ibge.gov.br/professores/

educa-recursos/20815-anamorfose.html>. Acesso em: 31 ago. 2020.

Desafio

Desafio

No dia 9 de março de 2024, o Instituto Brasileiro de Geografia e Estatística (IBGE) lançou uma nova versão do mapa-múndi, deixando as redes sociais em alvoroço. O motivo da surpresa é que, diferentemente dos mapas que estamos habituados a ver nos livros escolares ou até em rápidas buscas no Google, a nova versão traz o Brasil no centro do mundo.

PAISES MEMBROS DO G20



A SURPRESA COM O MAPA APRESENTADO É EXPLICADA POR ELE CONTRARIAR

Poliedro
Curso

Desafio

a) A convenção cartográfica, conjunto de regras que busca garantir a neutralidade de um mapa.

b) O etnocentrismo, doutrina socioespacial que defende simetria entre diferentes países em um mapa-múndi.

c) O eurocentrismo, visão de mundo que institui a Europa enquanto parte central e superior do mapa-múndi.

d) A orientação espacial, relação que usa a latitude e a longitude para oferecer precisão na construção de um mapa.

e) O regionalismo, exercício que define regiões segundo critérios sociais para a diagramação de um mapa-múndi.

Poliedro
Curso

Flws

Poliedro
Curso

Aviso de confidencialidade: conteúdo de propriedade intelectual do Poliedro Educação e suas unidades de negócios. Não deve ser copiado, compartilhado ou reproduzido sem o consentimento e autorização formal do Poliedro.