Poliedro
Curso

Semanas 01 e 02

Aviso de confidencialidade: conteúdo de propriedade intelectual do Poliedro Educação e suas unidades de negócios. Não deve ser copiado, compartilhado ou reproduzido sem o consentimento e autorização formal do Poliedro.

1. Espaço Geográfico



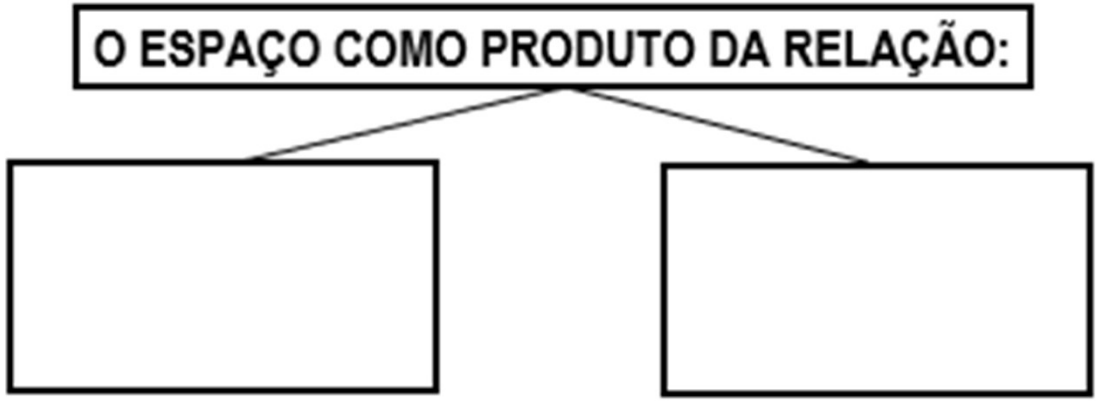

"Produzido pela sociedade de acordo com o nível de desenvolvimento e com os sistemas econômicos e sociais dominantes; ele é produzido visando alcançar determinados fins, aqueles que interessam ao sistema ou à formação econômico-social dominante".

O aprimoramento das técnicas modifica as formas de produção e apropriação do espaço geográfico

a) Correntes do Pensamento Geográfico:

a. 1 – Determinismo Geográfico (Ratzel – 1844 a 1904)

Destaca a influência que as condições naturais exercem sobre a humanidade – Para Ratzel o Estado é como um organismo vivo que precisa de espaço (_____)

<u>Proposta teórica:</u>

MAR DO NORTE
MAR BÁLTICO
ALEMANHA
Danzig
Setembro 1939
Março 1939
Outubro 1938
Março 1938
ALEMANHA
POLÓNIA
País dos Sudetas
CHECOSLOVÁQUIA
ÁUSTRIA
Limite máximo da expansão alemã em Setembro de 1939
0
200 km

a.2 – Possibilismo Geográfico (Vidal de La Blache – 1845 a 1918)

- A natureza passa a ser vista como fornecedora de possibilidades e o homem o principal agente geográfico.

- - O meio natural oferece um conjunto de possibilidades, e sua utilização depende dos costumes e das técnicas

(_____)

Proposta teórica:

a. 3 – Geografia Crítica (a partir de 1970)

- Pós 2ªGM: Guerra Fria e Descolonização da África e Ásia
- Uso do marxismo como método de análise;
- Rompimento da neutralidade e propõe engajamento e criticidade junto a toda a conjuntura social, econômica e política do mundo;
- Procura compreender as desigualdades, propor soluções e coloca o homem como principal agente de transformação espacial;

****** Grandes referências: Yves Lacoste e Milton Santos.**



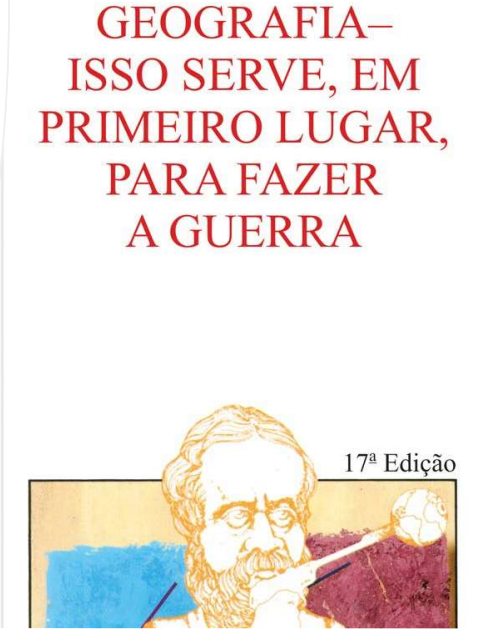



b) Características fundamentais do espaço geográfico

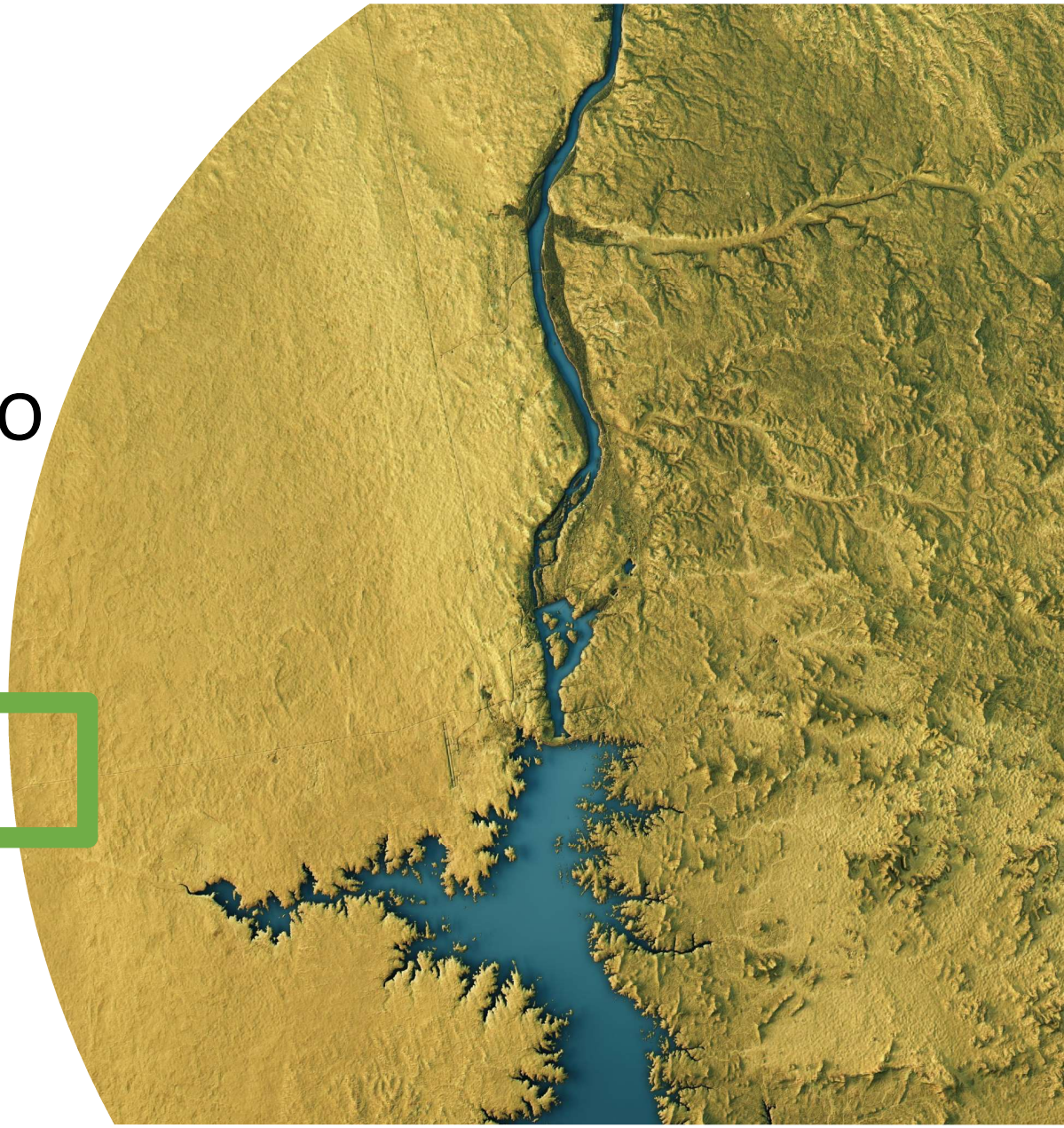

b.1 – Absoluto:

Espaço apenas como uma localização e formas (geografia descritiva)

b.2 - Relativo:

Espaço como conjunto de relações entre seres humanos e os objetos que o formam.

O uso e suas variáveis

b.3 – Produto e condição:

As relações sociais transformam o espaço e são transformadas pelo espaço.

b.4 - Dimensão temporal - acúmulo desigual de tempos

O espaço é resultado das ações humanas em diferentes momentos históricos.

Arcos da lapa: ***rugosidade*** *incorporada a paisagem da cidade do Rio de Janeiro.*

Concepção de espaço: Conjunto indissociável de sistemas de objetos (fixos) e de sistemas de ações (fluxos)

DICA:

2. Paisagem:



- Materialização dos processos naturais e sociais;
- Processo de apreensão seletivo (Senso Comum x Senso Crítico);
- Aparência da realidade (não sua explicação).

Capela dos Aflitos (1774/1779)

Endereço

Rua dos Aflitos , 70 - Traves. Rua dos Estudantes - alt. nº 52 , Liberdade

Poliedro Curso

Aviso de confidencialidade: conteúdo de propriedade intelectual do Poliedro Educação e suas unidades de negócios.
Não deve ser copiado, compartilhado ou reproduzido sem o consentimento e autorização formal do Poliedro.

3. Escala “categoria” de análise (escala geográfica – escala social)

→ **Local (lugar) – Região – “Nacional” - Global**

a) **Lugar :** Base da (re)produção da vida e das relações sociais

b) Região: Porção do espaço estabelecido segundo critérios de análise;

c) **Global:** Abrangência dos fenômenos (em todos os lugares e regiões)

OBSterritório:**

Espaço definido e delimitado por e a partir das relações de poder, dominação e apropriação que nele se instalam.

***** Palavra-chave:**

4. Desenvolvimento do Meio técnico-científico-informacional



Obs: Meio natural:

Período que vai do Neolítico (10.000 a.C e 3.000 a.C) – transformações lentas “tempo lento/tempo da natureza”

- Escala Local; Determinismo

Meio técnico:

- Século XVIII – 1ª Revolução Industrial (Inglaterra);
- Indústria 1.0;
- Mecanização “surgimento do espaço mecanizado”;
- Substituição da força animal;

➡ Aceleração do processo de produção e transformação do espaço geográfico

Meio técnico-científico:

- Século XIX – 2ª Revolução Industrial (Expansão pela Europa, Japão, EUA e Subcontinente Indiano)
- Indústria 2.0;

Meio técnico-científico-informacional:

- Século XX e XXI – 3ª e 4ª Revolução Industrial (O processo agora alcança América Latina, África e Ásia)

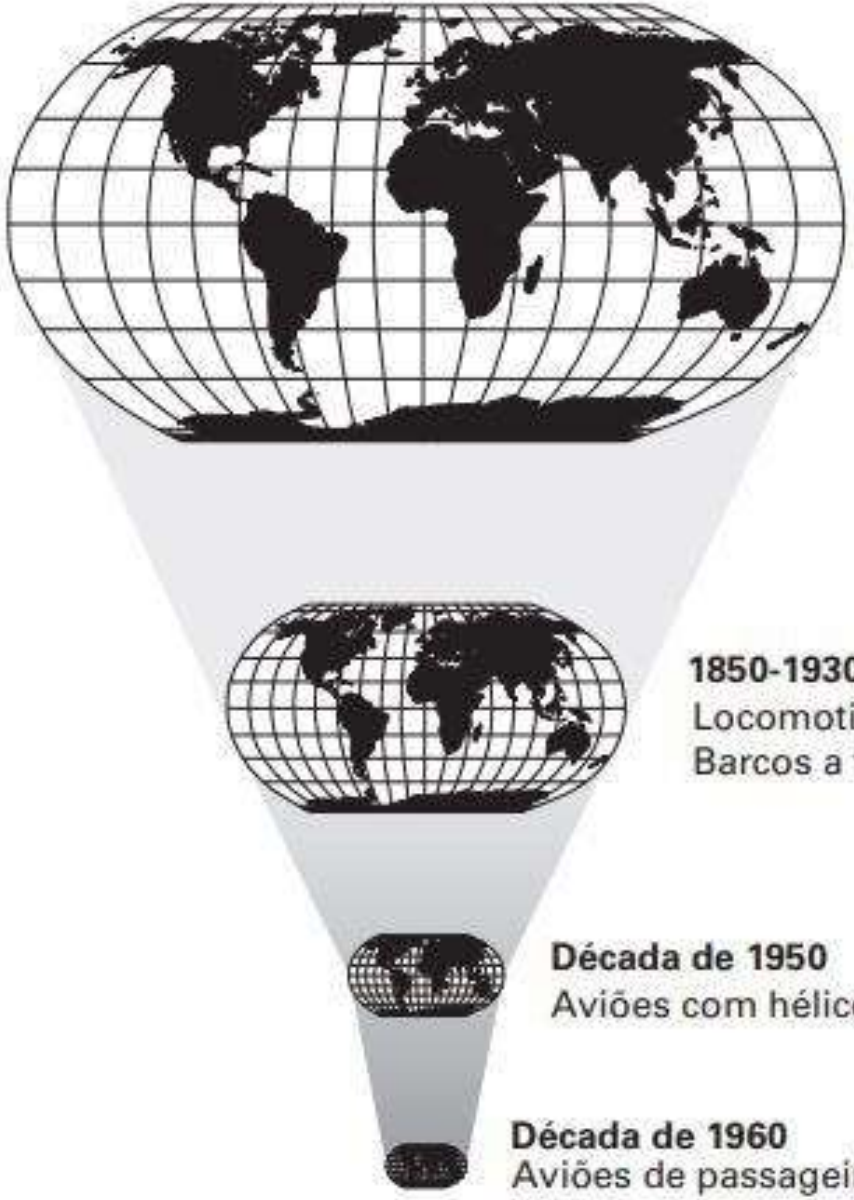

1500-1840
Velocidade média de veículos puxados por cavalos e navios a vela – 16 km por hora.

1850-1930
Locomotivas a vapor – média 100 km por hora.
Barcos a vapor – 25 km por hora.

Década de 1950
Aviões com hélices – 480-640 km por hora.

Década de 1960
Aviões de passageiros a jato – 800-1120 km por hora.