Semana 3

ANTIGUIDADE ORIENTAL

Prof. Guilherme Freitas

- **MODO DE PRODUÇÃO ASIÁTICO**

* Crescente fértil: berço da civilização / delta no rio Nilo, rios Tigre e Eufrates, rio Jordão
* Civilizações Hidráulicas ou "de regadio": dependência dos rios para agricultura

Crescente Fértil
Mediterrâneo
Biblos
Sidon
Tiro
Damasco
Jerusalém
Corredor Sírio-Palestiniano
Sais
Mênfis
EGIPTO
Nilo
Tebas
Trópico de Câncer
Nilo
Mar Vermelho
Tigre
Ninive
Assur
Eufrates
MESOPOTÂMIA
Babilónia
Golfo Pérsico
0 200 400 600 kilómetros
0 200 400 milhas

Mar Negro
Mar Cáspio
Anatólia
ASSÍRIA
Média
Mar Mediterrâneo
FENÍCIA
Crescente Fértil
Tigre
MESOPOTÂMIA
Levante
Eufrates
Deserto Sírio
Baixo Egito
Golfo Pérsico
Alto Egito
Nilo
Mar Vermelho
Deserto da Núbia
0
250
500
1000

- **MODO DE PRODUÇÃO ASIÁTICO**

* Crescente fértil: berço da civilização / delta no rio Nilo, rios Tigre e Eufrates, rio Jordão
* Civilizações Hidráulicas ou "de regadio": dependência dos rios para agricultura
* Estado teocrático (poder justificado através da religiosidade) e aristocrático (poder justificado através da posse da terra)

- **MODO DE PRODUÇÃO ASIÁTICO**

* Sociedade Estamental: hierarquizada por critério de sangue (nascimento) / formação de uma nobreza hereditária
* Religião politeísta: crença em múltiplos deuses
* Trabalho compulsório: Servidão de Estado (podendo ter escravidão por guerra ou trabalho assalariado)

- **MESOPOTÂMIA**

* Localização: região entre os rios Tigre e Eufrates (local extremamente fértil / disputado por povos locais e estrangeiros)
* Sucessão de povos na região: Sumérios, Acadianos, Amoritas (Primeiro Império Babilônico), Assírios, Caldeus (Segundo Império Babilônico)

SUMER

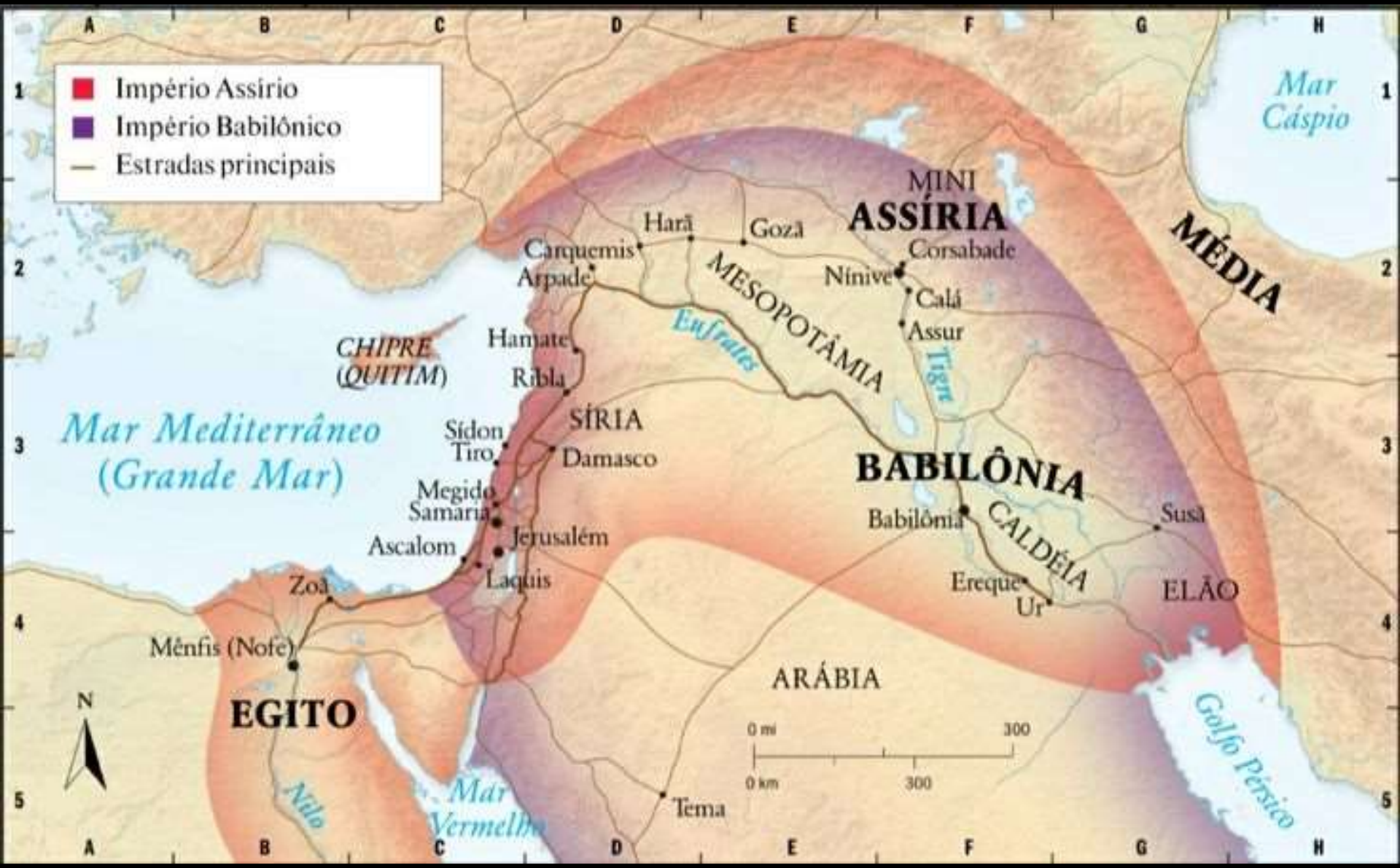
Império Assírio
Império Babilônico
Estradas principais
Mar Cáspio
MINI
ASSÍRIA
MÉDIA
Harã
Gozã
Carquemis
Arpade
Corsabade
Nínive
Calá
Assur
MESOPOTÂMIA
Eufrates
Tigre
CHIPRE
(QUITIM)
Hamate
Ribla
SÍRIA
Mar Mediterrâneo
(Grande Mar)
Sídon
Tiro
Damasco
BABILÔNIA
Megido
Samaria
Jerusalém
Ascalom
Laquis
Babilônia
CALDÉIA
Susã
Zoã
Ereque
Ur
ELÃO
Mênfis (Nofe)
EGITO
ARÁBIA
N
0 mi
300
0 km
300
Golfo Pérsico
Nilo
Mar Vermelho
Tema

6. O Novo Império Babilônico e o Reino do Egito

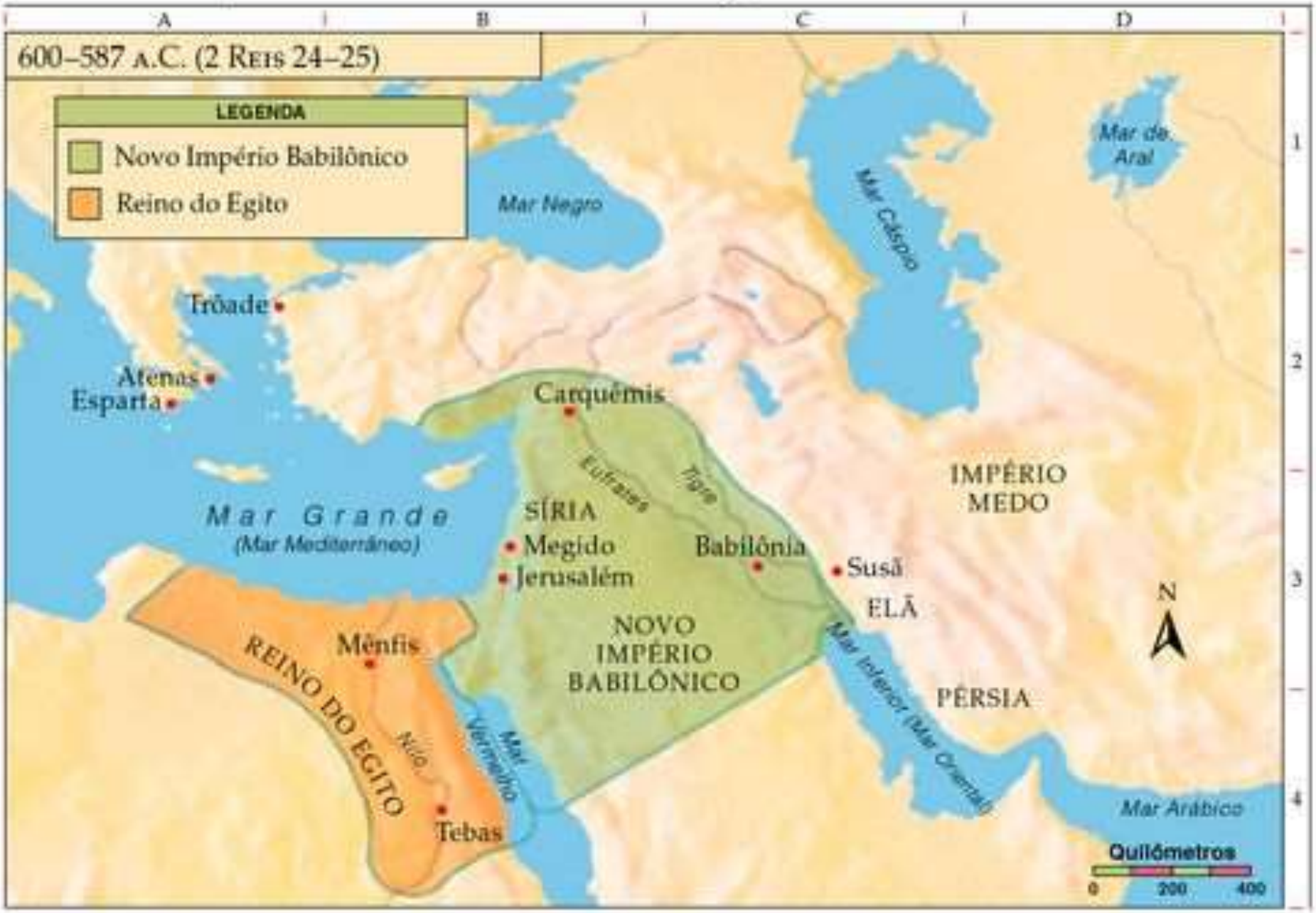

- **MESOPOTÂMIA**

* Localização: região entre os rios Tigre e Eufrates (local extremamente fértil / disputado por povos locais e estrangeiros)
* Sucessão de povos na região: Sumérios, Acadianos, Amoritas (Primeiro Império Babilônico), Assírios, Caldeus (Segundo Império Babilônico)
* Escrita Cuneiforme: primeira forma de escrita da história

Escrita cuneiforme suméria.

- **MESOPOTÂMIA**

* Arquitetura monumental em tijolos (destaque aos Zigurates)

Zigurate de Ur

- **MESOPOTÂMIA**

* Arquitetura monumental em tijolos (destaque aos Zigurates)
* Epopeia de Gilgamesh: mais antiga obra literária

Epopeia de Gilgamesh

- **MESOPOTÂMIA**

* Arquitetura monumental em tijolos (destaque aos Zigurates)
* Epopeia de Gilgamesh: mais antiga obra literária
* Código de Hamurabi (1772 a.C.): primeiro código jurídico de leis escritas da história (Lei do Talião / diferentes penas para diferentes classes sociais)

Código de Hamurabi (1772 a.C.).

- **IMPÉRIO EGÍPCIO**

* Localização: margens norte do Rio Nilo (cheias regulares - fertilidade, isolamento geográfico)

MAR MEDITERRÂNEO
CHIPRE
Biblos
Sídon
Tiro
FENÍCIA
Jericó
Jerusalém
Jordão
PALESTINA
Eufrates
Mari
ACÁDIA
Babilónia
DELTA
EGIPTO
Gizé
MÊNFIS
Deserto Líbio
BAIXO EGIPTO
Deserto Arábico
SINAI
Nilo
TEL-AL-AMARNA
ALTO EGIPTO
Abidos
Karnak
Vale dos Reis
TEBAS
Luxor
Edfu
Mar Vermelho
ARÁBIA
Assuão
1ª Catarata
Abu-Simbel
2ª Catarata

- **IMPÉRIO EGÍPCIO**

* Localização: margens norte do Rio Nilo (cheias regulares - fertilidade, isolamento geográfico)
* Ritualização da política: Estado teocrático
* Forte influência política e social dos sacerdotes



O Escriba Sentado, 2600 a.C. Museu do Louvre, Paris, FRA.

- **IMPÉRIO EGÍPCIO**

* Localização: margens norte do Rio Nilo (cheias regulares - fertilidade, isolamento geográfico)
* Ritualização da política: Estado teocrático
* Forte influência política e social dos sacerdotes
* Escrita hieroglífica: escrita administrativa ou religiosa / definição de status / poder político dos Escribas

- **IMPÉRIO EGÍPCIO**

* Arquitetura monumental em pedras
* Arte Mortuária / mumificações / figuras antropozoomórficas

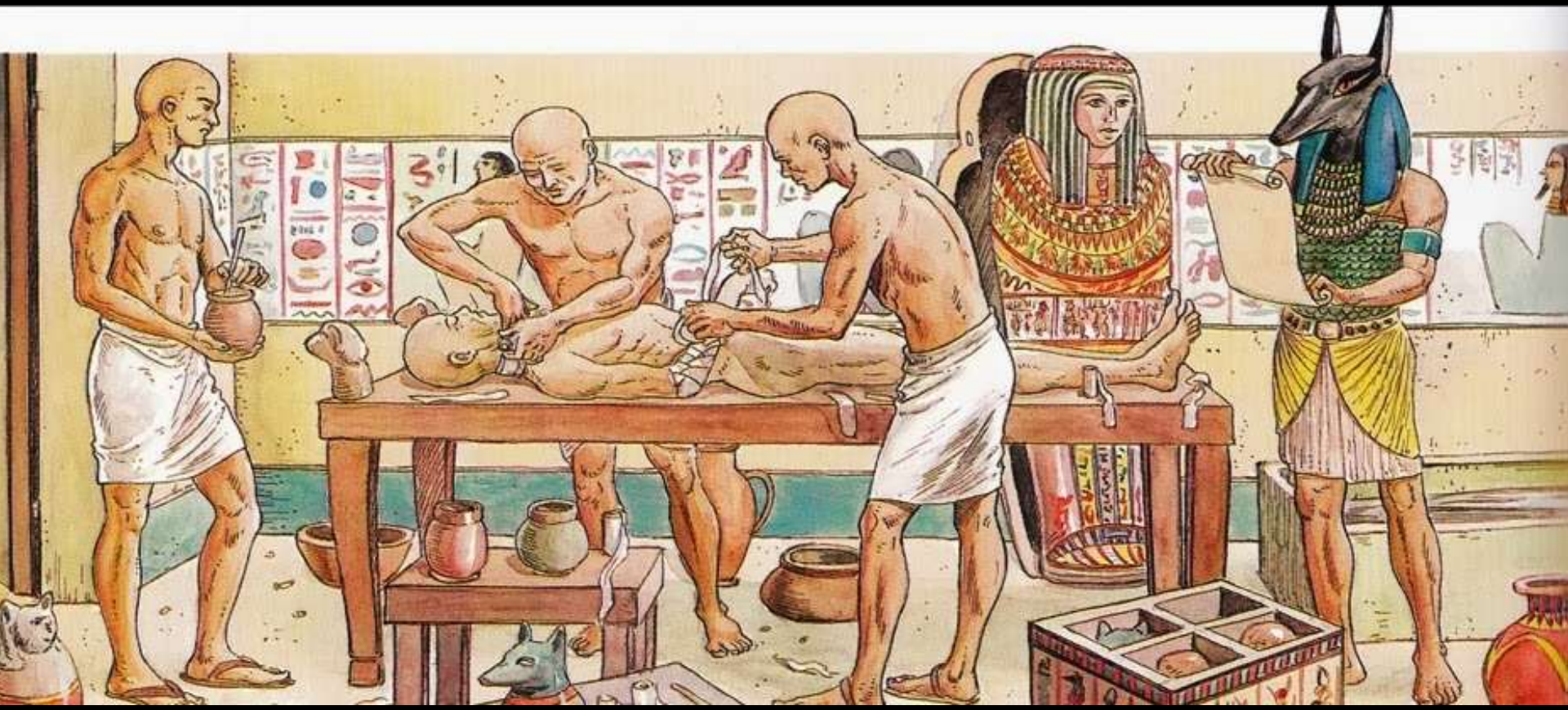

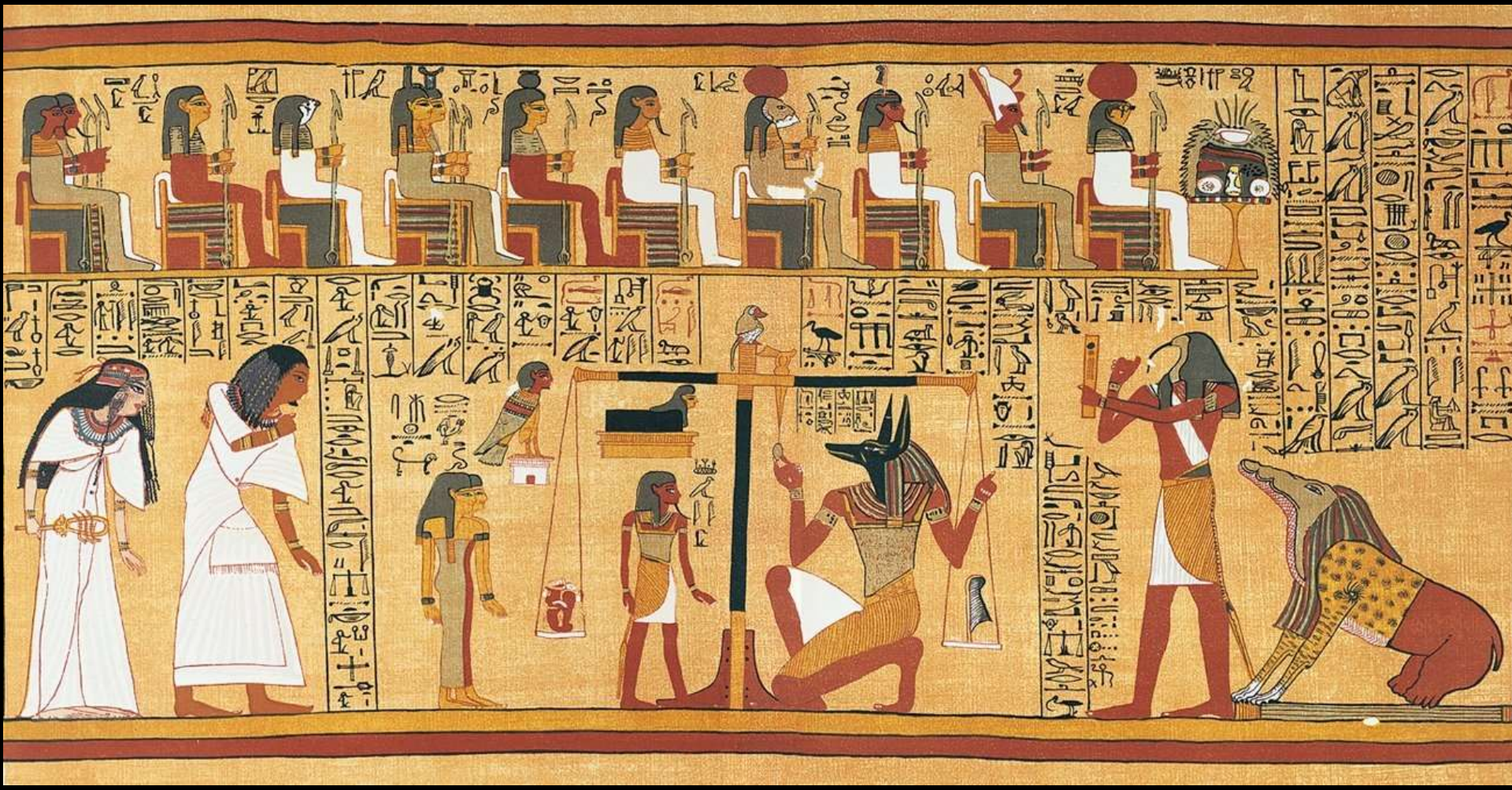

Papiro de Ani, 1250 a.C.
Museu Britânico, Londres, ING.



Pedra de Roseta (Egito Tardio). Documento que permitiu a tradução dos hieróglifos durante o mundo contemporâneo.

Múmia egípcia no Museu Britânico.

As Pirâmides da Necrópole de Gizé

A Esfinge da Necrópole de Gizé

Amenófis IV (1388-1335 a.C.). Amenófis IV foi responsável por uma reforma religiosa no Egito que implantou o monoteísmo e tentou combater o poder dos sacerdotes através do fim ao extenso panteão de deuses egípcios. A partir da reforma, o único deus passou a ser Aton e Amenófis passou a se chamar Akhenaton.

Busto de Nefertiti, 1345 a.C.
Museu Egípcio de Berlim.



Máscara mortuária do Imperador Tutancâmon (1332–1323 a.C.). O túmulo do antigo faraó foi encontrado intacto em 1922.

- **IMPÉRIO EGÍPCIO**

* Arquitetura monumental em pedras
* Arte Mortuária / mumificações / figuras antropozoomórficas
* Reino de Kush: civilização nas margens sul do Rio Nilo (atual Sudão e Núbia) / disputas territoriais e forte influência na sociedade egípcia

Mar Mediterrâneo
Reino egípcio
Mar Vermelho
Kush
Axum

Imperio egipcio
Siglo XV a. de C.
Mar Negro
Mar Caspio
IMPERIO HITITA
Sardes
Micenas
CILICIA
ASIRIA
Carchemish
Nínive
Assur
SIRIA
Citium
MESOPOTAMIA
Mar Mediterráneo
Biblos
Kadesh
Sidón
Damasco
Tiro
CANAÁN
Babilonia
Nippur
Ur
Gaza
Tanis
Avaris
SINAÍ
Golfo Pérsico
Menfis
Heliópolis
LIBIA
Nilo
Heracleópolis
ARABIA
Imperio
Abydos
TEBAS
Asuán
Elefantina
Mar Rojo
Abú Simbel
II
egipcio
KUSH
III
IV
Napata
V
VI
PUNT
(influencia egipcia)

Necrópole de Meroê, Kush.



Necrópole de Meroê, Kush.

- **FENÍCIOS**

* Localização inicial: atual Líbano
* Atividade base: Comércio Marítimo (elite talassocrática)
* Organização em cidades-Estado: colônias fenícias espalhadas pelo litoral do Mar Mediterrâneo

As rotas comerciais dos fenícios
Fenícia
Rotas comerciais
Oceano Atlântico
EUROPA
Mar Adriático
Mar Negro
IBÉRIA
ÁSIA
Mar Egeu
Gadir
Tingis
Cartago
SICILIA
Mar Mediterráneo
CRETA
CHIPRE
Biblos
Sídon
Tiro
ÁFRICA
Léptis
Cirene
Mênfis
N
0
500 km
0
300 miles

- **FENÍCIOS**

* Localização inicial: atual Líbano
* Atividade base: Comércio Marítimo (elite talassocrática)
* Organização em cidades-Estado: colônias fenícias espalhadas pelo litoral do Mar Mediterrâneo
* Formação de um alfabeto funcional fonético / posterior contato com os gregos e influência no alfabeto ocidental atual

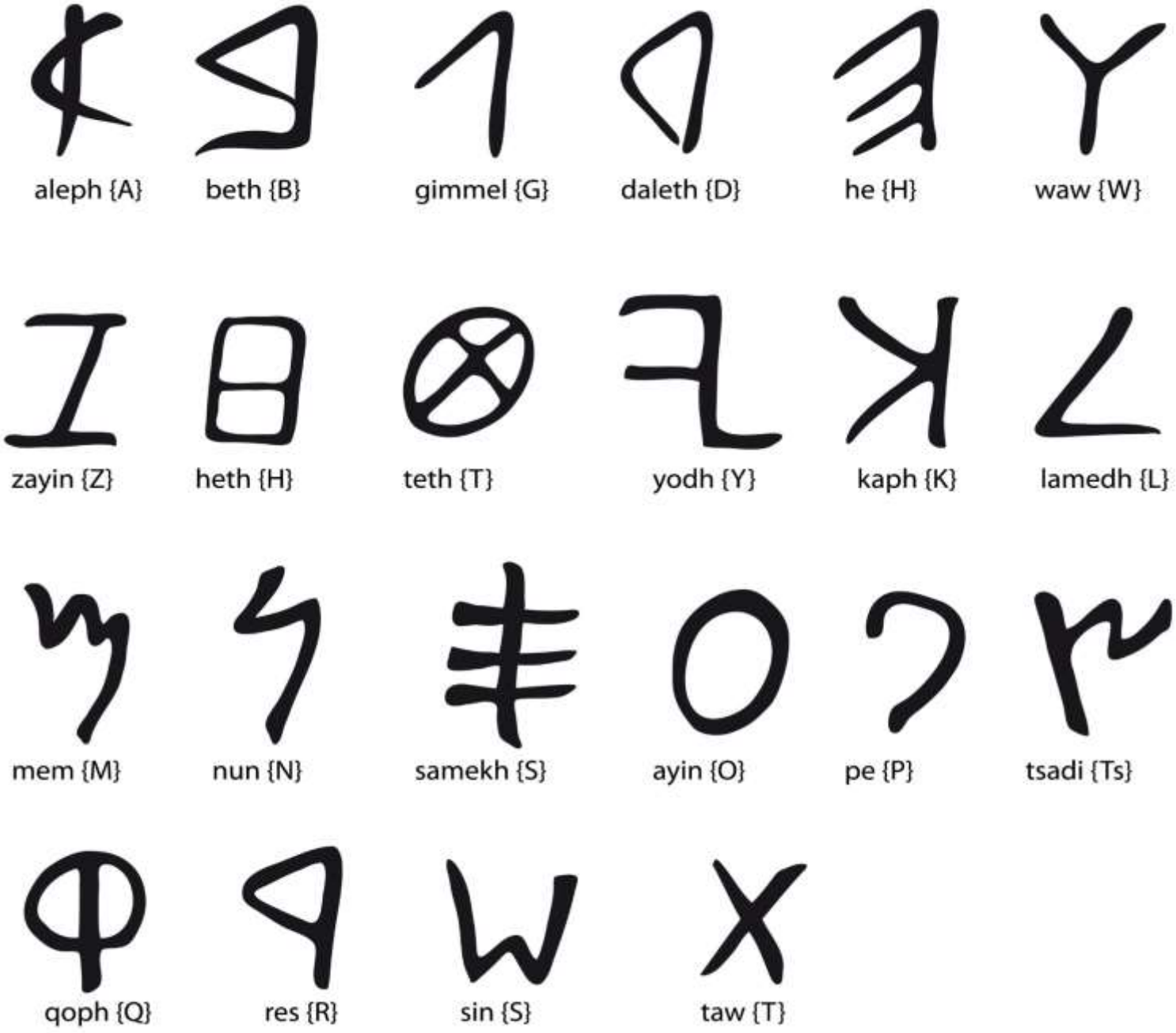
aleph {A}
beth {B}
gimmel {G}
daleth {D}
he {H}
waw {W}
zayin {Z}
heth {H}
teth {T}
yodh {Y}
kaph {K}
lamedh {L}
mem {M}
nun {N}
samekh {S}
ayin {O}
pe {P}
tsadi {Ts}
qoph {Q}
res {R}
sin {S}
taw {T}

- **HEBREUS**

* Localização: atual Palestina / Israel
* Religião monoteísta e povo agropastoril
* Base historiográfica: Antigo Testamento / discussões entre os aspectos religiosos e científicos

Moses and the Tablets, by Jerry Harston, © IRI

- **IMPÉRIO PERSA**

* Localização: atual Irã
* Império centralizado / Auge: imperialismo e domínio sobre a região da Crescente Fértil

Assyrie
Khorsabad
10c

Imperio persa
ESCITIA
Mar Negro
Mar Caspio
MACEDONIA
TRACIA
Bizancio
Easis
GRECIA
Maratón
Salamina
Atenas
LIDIA
Sardis
ARMENIA
ASIRIA
CILICIA
Tarso
Isos
Carquemis
Ninive
MEDIA
HIRCANIA
MTES. ELBURZ
Maracanda
(Samarcanda)
SOGDIANA
BACTRIANA
PARTIA
ARIA
Eufrates
Tigris
Tadmor
SIRIA
Sidón
Tiro
Damasco
Jerusalén
Echbatana
(Acmeta)
MTES. ZAGROS
DRANGIANA
ARACOSIA
Mar Mediterráneo
(Mar Grande)
Cirene
LIBIA
Babilonia
Susa
ELAM
Persépolis
Pasargada
Menfis
(Nof)
EGIPTO
Elat
(Elot)
ARABIA
Temá
PERSIA
Golfo Pérsico
Indo
GEDROSIA
INDIA
Nilo
Mar Rojo
No-amón
(Tebas)
Siene
N
0 mi
500
0 km
500
A
B
C
D
E
F
G
H
1
2
3
4
5

- **IMPÉRIO PERSA**

* Localização: atual Irã
* Império centralizado / Auge: imperialismo e domínio sobre a região da Crescente Fértil
* Expansão para o ocidente ao longo do século V a.C. e conflito com as cidades gregas

Abdera
Pella
Sestos
Lampsacos
Abydos
Larisa
Ambracia
498 aC
480 aC
Pergamo
Mitilene
Tebas
Eretria
490 aC
479 aC
Sardis
Focea
Chios
498 aC
Megara
Atenas
Elis
Corinto
488 aC
Efeso
498 aC
479 aC
Olimpia
Tegea
Argos
Mileto
Mylas
Esparta
Naxos
Halicarnaso
Mesene
Rodes
Legenda
Vitória grega
Vitória persa
Batalha indecisa
Império persa de 500 aC
Conquistas persas 492 aC
Os aliados gregos
A expedição de Xerxes (480-479 aC)
A expedição de Dates y Artaphernes (498-490 aC)
Cidades gregas que lutaram contra a Pérsia
Cidades gregas aliadas com a Pérsia
Cidades gregas que evoltaram-se contra o império persa
Outras cidades importantes

- **IMPÉRIO PERSA**

* Localização: atual Irã
* Império centralizado / Auge: imperialismo e domínio sobre a região da Crescente Fértil
* Expansão para o ocidente ao longo do século V a.C. e conflito com as cidades gregas
* Zoroastrismo: religião dualista (bem X mal)

Semana 3

ANTIGUIDADE ORIENTAL

Prof. Guilherme Freitas